flotimatics
Innovación Telemática (https://flotimatics.com/)

GEOTAB
Solución Integral de Telemetría
Transporte de Carga | Tecnología Geotab Certificada

Más Allá del GPS Tradicional

Flotimatics + Geotab ofrece una plataforma integral que conecta directamente con el motor de sus unidades, entregando datos precisos del ECM, hábitos de manejo objetivos y cumplimiento de rutas certificado. No vigilamos operadores, optimizamos operaciones.

Flotimatics. Tecnología Superior a un GPS tradicional

①

Información de Motor

Datos directos del ECM sin estimaciones ni cálculos aproximados:

- Odómetro real del motor
- Voltajes y nivel de batería
- Temperatura del motor y del aceite
- Litros consumidos exactos
- Nivel de combustible en tiempo real
- Rendimientos por viaje y por operador
- RPMs y velocidad gobernada

②

Fallas de Motor

Alertas preventivas y diagnóstico en tiempo real:

- Alertas de calentamiento del motor
- Nivel bajo de combustible
- Voltajes insuficientes
- Alertas de mantenimiento programado
- Códigos DTC activos e históricos
- Parámetros críticos fuera de rango

③

Hábitos de Manejo y Detección de Accidentes

Registro objetivo de eventos críticos:

- Giros bruscos con ubicación GPS
- Frenadas bruscas y aceleraciones agresivas
- Notificación de accidentes en tiempo real
- Detección de posibles accidentes
- Contexto completo de cada evento
- Datos forenses para análisis

④

Información Detallada de Viajes

Trazabilidad total sin interpretaciones:

- Recorridos en alta definición
- Movimientos en patios y zonas sin cartografía
- Horarios exactos de salidas y llegadas
- Detenciones con duración precisa
- Rendimientos por viaje completo
- Algoritmo que recrea fielmente cada movimiento

Diferenciadores Tecnológicos de la Plataforma Geotab

①

Fácil
Instalación

Instalación Plug & Play (https://static.wixstatic.com/media/f25fed_246c733e0e224a2c938ab9e808a12905~mv2.png)

Sencilla, no invasiva

No interfiere con garantías (https://static.wixstatic.com/media/f25fed_0efc61a9ff9a4a03907da7dc04689b22~mv2.png)

Gobernada por usted mismo

Accesorios de instación independiente

②

Visualización en Base a Movimientos

Interface fácil de utilizar

Active Tracking

Reglas 100 % configurable

Zonas y usuarios ilimitados

Recreación de accidentes

APP móvil

Active Tracking

③

SDK
(Kit de Desarrollo)

Extracción de información (https://developers.geotab.com/myGeotab/introduction/)

Integración en sistemas propios

SDK para clientes

Web Services inmediatos

IA para desarrollos

Market Place (https://marketplace.geotab.com/)

④

Planes Ajustados
a Necesidades

Soluciones escalables

Flexibles y adaptables

Ajustados a presupuesto

Planes de Financiamiento (https://flotimatics.com/propuesta-comercial-bundle/)

Contratos flexibles

⑤

Expansión Plug&Play y Paulatina

Paro de motor

Botón de pánico

Identificador de choferes

Sensores inalámbricos (Temperatura, Combustible, TPMS, etc)

Identificación de remolques

Cámaras con IA

Capacidades Forenses de Alto Nivel: Algoritmo Patentado de Movimientos

Caja Negra Automotriz Geotab GO

Similar a la de un avión comercial, cada unidad cuenta con una caja negra que registra continuamente:

- Velocidades exactas y por segundo
- Frenadas bruscas y aceleraciones agresivas
- Giros violentos y fuerzas G en impactos
- RPMs y comportamiento del motor
- Eventos de colisión con datos forenses
- Fecha, hora, minuto y segundo exactos
- Algoritmo patentado para recrear fielmente todos los movimientos del vehículo

La evolución del GPS tradicional

No solo sabemos DÓNDE estuvo el vehículo, sino CÓMO se condujo, con qué intensidad, y podemos recrear el incidente completo para análisis forense.

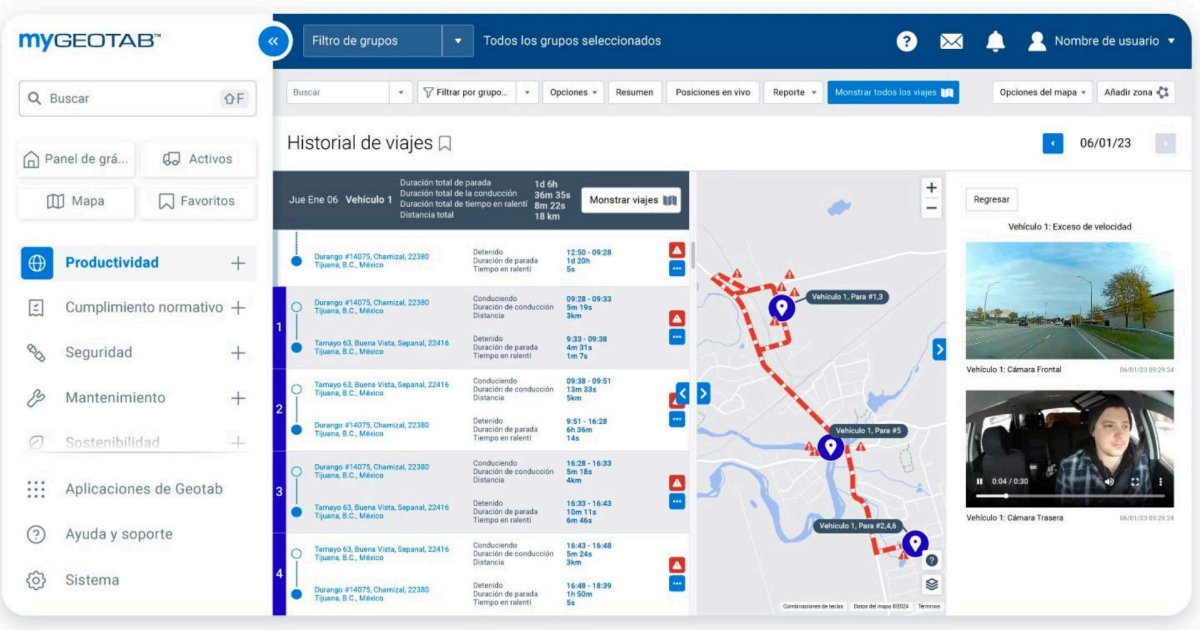

Esto permite:

> **Determinar Responsabilidades**

Evidencia objetiva e irrefutable para procesos legales y administrativos con valor probatorio.

Proteger a Operadores

Respaldo técnico ante acusaciones falsas, malinterpretaciones o denuncias infundadas.

Sustentar Auditorías

Información forense completa para órganos de control interno y externo.

100	24/7	GPS	100%
Registros por segundo en eventos críticos	Monitoreo continuo en tiempo real	Ubicación exacta con cada registro	Evidencia verificable y defendible

Una plataforma de gestión integral

Condiciones del Motor en Tiempo Real

Conexión directa al ECM vía J1939/J1708 sin corte de cables. Información crítica disponible 24/7 desde cualquier ubicación.

Fallas Activas

Códigos de diagnóstico (DTC) en tiempo real. Alertas automáticas a mantenimiento cuando se detecta un problema.

Fallas Históricas

Registro completo de códigos pasados, útil para mantenimiento preventivo y análisis de recurrencias.

Temperaturas Críticas

Monitoreo de temperatura del motor, aceite, refrigerante. Prevención de sobrecalentamientos.

Parámetros del Motor

RPM, presión de aceite, carga del motor, voltaje de batería, consumo instantáneo.

Alertas Preventivas

Notificaciones automáticas cuando un parámetro sale de rango. Prevención de averías costosas.

Mantenimiento Predictivo

Programación basada en horas de motor, kilómetros reales y condiciones de operación.

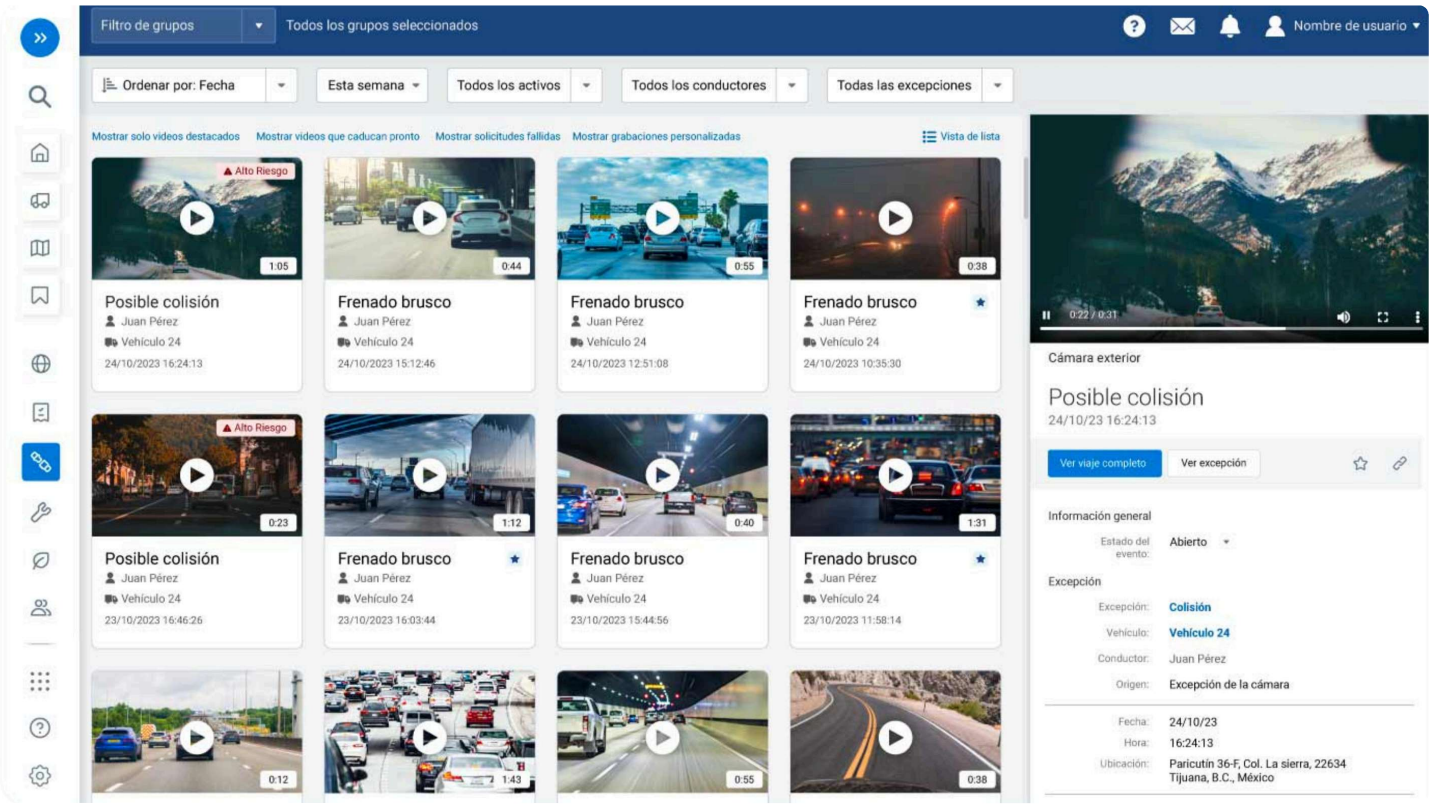

Plataforma de gestión de videos

Análisis en tiempo real

Cámaras Surfsight: Detección Automática de Eventos

Videoanalítica con Inteligencia Artificial para Casos Críticos

Cámara dual: vista al camino y al conductor

Detección Automática por IA:

- **Uso de dispositivo móvil** durante conducción
- **Conducción distraída** (desatención visual)
- **Mensajeando o escribiendo** al volante
- **Consumiendo alimentos** durante servicio
- **Fumando** en el vehículo oficial
- **Omisión de cinturón** de seguridad
- **Indicadores de fatiga** o somnolencia
- **Vehículo cercano** (riesgo de colisión)
- **Eventos de impacto** y colisiones

Funcionalidades del Sistema:

- **Grabación de contexto:** 15 seg antes/durante/después
- **Botón de pánico:** Activación manual en emergencias
- **Video en tiempo real:** Transmisión en vivo
- **Almacenamiento:** 7 a 30 días de video continuo
- **Clasificación automática:** Por nivel de riesgo
- **Evidencia objetiva:** Video, imagen, fecha, hora, ubicación y velocidad
- **Protección legal:** Defensa ante denuncias y garantía de transparencia

Sistema de videoanalítica instalado en vehículo

Protección y Transparencia

Video objetivo para proteger al operador ante denuncias sin fundamento y garantizar transparencia ante ciudadanía.

Ejemplos de Detección por Inteligencia Artificial

Ejemplos de Detección por Inteligencia Artificial

Haga clic en cada video para reproducirlo en una nueva pestaña:

Sin Cinturón de Seguridad

(https://docs.google.com/file/d/17oDJfcXcQt2ht4BkTUUPMUvLI_tp_c6)



Riesgo de Colisión

(https://docs.google.com/file/d/1g9UZVjLqpG2-6Z_8-1bCVxwrpQMcd-ci/preview)

Conducción Defensiva

(https://docs.google.com/file/d/18Q7SK1t0nVdIB6Dwq3fz1FLcFd3BvUi

Uso de Celular

(https://docs.google.com/file/d/1MYMmZ9flYrMPSu_zc0fLpoI5nrY630)

Colisión Grave

(https://video.wixstatic.com/video/f25fed_917fc351475042ca8880a321

Cruce de Camellón

(https://video.wixstatic.com/video/f25fed_36b9d47d35e24f5ea6764d4

Conducción Distraída

(https://video.wixstatic.com/video/f25fed_2ce2092919224cabbf6a3cca

Uso de celular

(https://video.wixstatic.com/video/f25fed_75ebfb2f1c4b4c37a4071914

Velocidad 144 km/h

(https://video.wixstatic.com/video/f25fed_139d6363ab794dfc8822167b

Movimiento Brusco

(https://video.wixstatic.com/video/f25fed_5f071f747cf74c65be7a3284c

Conducción distraída y fumando

(https://video.wixstatic.com/video/f25fed_39dffee84cbb43bd9b736032

Uso de celular (2)

(https://video.wixstatic.com/video/f25fed_75ebfb2f1c4b4c37a4071914

Soluciones y Tecnologías Disponibles

Videotelemática

Detector de Jammer

Ver más ▸ (https://f25fed3e-603f-4e5c-a98e-b226c7d129a1.usrfiles.com/ugd/f25fed_1796399916844ed8b6de529ab4987c9d.pdf)

Ver más ▸ (https://f25fed3e-603f-4e5c-a98e-b226c7d129a1.usrfiles.com/ugd/f25fed_b8035496ce524391b2ce138574e2f3fd.pd

Gestión de Motores

Ver más ▸ (https://f25fed3e-603f-4e5c-a98e-b226c7d129a1.usrfiles.com/ugd/f25fed_298c50bcaf374d008e1c5837520bb3db.pdf)

Tracklight

Ver más ▸ (https://f25fed3e-603f-4e5c-a98e-b226c7d129a1.usrfiles.com/ugd/f25fed_63e24dd5714f4644bdd4d7cfe66658dc.p

Centro Técnico: Fichas Descargables

Dispositivo GO9

PDF ▸ (https://f25fed3e-603f-4e5c-a98e-b226c7d129a1.usrfiles.com/ugd/f25fed_4c9546b106384baab27b859350861756.pdf)

GO para uso rudo

PDF ▸ (https://f25fed3e-603f-4e5c-a98e-b226c7d129a1.usrfiles.com/ugd/f25fed_716f2683b2cd4dcb9927a2d6789185c9.pdf)

b22

Lectora de conductor

PDF ▸ (https://f25fed3e-603f-4e5c-a98e-b226c7d129a1.usrfiles.com/ugd/f25fed_1a67254381f64b77a470a8c04293e345.pdf)

Iridium Satelital

PDF ▸ (https://f25fed3e-603f-4e5c-a98e-b226c7d129a1.usrfiles.com/ugd/f25fed_8a4278908aaf4d6087266870efdf067e.pdf)

b22

IOX HID

PDF ▸ (https://f25fed3e-603f-4e5c-a98e-b226c7d129a1.usrfiles.com/ugd/f25fed_02f073d6c14245fb98ab6070c5013167.pdf)

IOX GARMIN

PDF ▸ (https://f25fed3e-603f-4e5c-a98e-b226c7d129a1.usrfiles.com/ugd/f25fed_ec7bf0ccf432450ea659f8ac145fb803.pdf)

b22

IOX-GOTALK

PDF ▸ (https://f25fed3e-603f-4e5c-a98e-b226c7d129a1.usrfiles.com/ugd/f25fed_8676e0f7a5334cc5b5eae1f3354d0dfc.pdf)

Instalación KIT - Reefer

PDF ▸ (https://f25fed3e-603f-4e5c-a98e-b226c7d129a1.usrfiles.com/ugd/f25fed_63f7f5e0b6c2421bb5221a5293afe361.pdf)

Beneficios Cuantificables para Transporte de Carga

Reducción de Costos Operativos

- Ahorro de 10-20% en combustible mediante monitoreo de hábitos
- Reducción de 30% en ralentí innecesario
- Disminución de 25% en multas por exceso de velocidad

- Optimización de rutas ahorra 15% en kilometraje

Prevención de Riesgos

- Reducción de 40% en accidentes con videotelemetría
- Disminución de 50% en robo de unidades y carga
- Detección temprana de fallas mecánicas
- Evidencia legal que protege a la empresa

Optimización de Mantenimiento

- Mantenimiento basado odómetro y horas reales del motor
- Alertas preventivas de fallas del ECM
- Reducción de paros no programados en 35%
- Extensión de vida útil de componentes

Mejora en Servicio al Cliente

- ETAs precisos en tiempo real
- Notificaciones automáticas de llegada
- Prueba de entrega geolocalizada
- Transparencia total en el proceso logístico

Inteligencia Artificial Integrada: El Nuevo Estándar en Gestión de Flotas

Cada unidad genera miles de datos todos los días. Pero tener datos no es tener control.

El verdadero poder está en entenderlos en segundos.

Geotab no solo recopila información — ahora la interpreta contigo.

Pregúntale directamente a tu operación

En lugar de buscar en reportes, obtienes respuestas en segundos:

- "¿Qué operador está manejando de forma más agresiva?"
- "¿Qué unidad consume más combustible en ralentí?"
- "¿Dónde estoy teniendo más eventos de riesgo esta semana?"
- "¿Cuál fue el impacto real de ese accidente?"
- "¿Qué rutas están generando más tiempo improductivo?"
- "¿Qué unidades requieren mantenimiento urgente?"
- "¿Cuánto estoy gastando en excesos de velocidad este mes?"

> **Próximamente: comunicación por voz con tus operadores**
> El sistema detecta un riesgo y habla directamente con el conductor — sin que nadie levante el teléfono.

Sin filtros. Sin reportes interminables. Sin depender del analista.

La IA trabaja donde otros sistemas no llegan

OTROS SISTEMAS	GEOTAB CON IA
Muestran mapas	Detecta patrones
Generan reportes	Prioriza riesgos
Te llenan de gráficas	Resume lo importante
Tú tienes que interpretar todo.	Te dice dónde actuar

IA que interactúa en tiempo real

Cuando detecta un riesgo, no solo manda una alerta. Puede:

- Advertir al operador en tiempo real
- Guiarlo en caso de incidente
- Activar protocolos automáticamente
- Generar evidencia inmediata

"Esto ya no es solo telemetría. Es evolución tecnológica aplicada a la rentabilidad y seguridad de tu operación."

OTROS PROVEEDORES	GEOTAB CON IA
Entregan datos · Muestran lo que pasó	Entrega decisiones · Anticipa lo que puede pasar

Flotas Líderes que Confían en Geotab

Más de 6 millones de vehículos conectados en todo el mundo. Empresas globales de clase mundial confían en la tecnología Geotab para gestionar sus flotas.

Implementación Escalable y Flexible

Programa Piloto

Inicio con un grupo de unidades para validar resultados antes de escalar a toda la flota.

Crecimiento Modular

Agregue funcionalidades según necesidades: primero telemetría básica, luego cámaras, sensores, RFID.

Reglas Personalizadas

Configuración específica por tipo de unidad, ruta, operador, zona geográfica.

Reportes Automáticos

Informes programados enviados a gerentes, operaciones, mantenimiento, finanzas.

Integración con ERP y Sistemas propios

API abierta para conexión con sistemas de gestión existentes.

Plataforma en la Nube

Acceso desde cualquier ubicación sin infraestructura de servidores locales.

No se trata de vigilar operadores, sino de optimizar operaciones

La telemetría proporciona información objetiva para tomar mejores decisiones, proteger a los operadores ante falsas acusaciones, reducir costos operativos y mejorar la rentabilidad del negocio.

Información de Contacto

Socio estratégico en telemetría

Oficinas Corporativas

Business Center
Torre V1
Oficinas 307 & 315
Av. Universidad 234
Durango, Dgo.
CP 34110

Canales de Comunicación

Tel: 800 FLOTIMA | 618 828 8632
consultoria@flotimatics.com (mailto:consultoria@flotimatics.com)
soporte@flotimatics.com (mailto:soporte@flotimatics.com)

Redes Profesionales

www.flotimatics.com (https://www.flotimatics.com/)
Facebook (https://www.facebook.com/share/16AWnCSDAk/?mibextid=wwXIfr)
Instagram (https://www.instagram.com/flotimaticssadecv?igsh=MTBodmg0d2k1aWcxYg==)
LinkedIn (https://www.linkedin.com/company/flotimaticsmx/)
YouTube (https://www.youtube.com/@flotimatics1168)